Image Reference: Tanakit Intaniyom (03/07/2017)

TRAVEL GUIDE ToBeIT#61

By Tanakit Intaniyom(DSBA 60070141)

Updated V1.1 (13/10/2017)

Copyright (c) 2017. Free for education use.

INTRODUCTION

WELCOME! ยินดีต้อนรับ

ยินดีต้อนรับน้องๆสู่คณะเทคโนโลยีสารสนเทศ
สถาบันเทคโนโลยีพระจอมเกล้าเจ้าคุณทหารลาดกระบัง

เอกสารนี้จัดทำขึ้นเพื่อประโยชน์ของน้องๆในการเดินทางมายัง ToBeIT#61 ที่คณะเทคโนโลยีสารสนเทศของเรา จุดประสงค์ก็คือเพื่อป้องกันการพลัดหลง ความสะดวกสบาย และความปลอดภัยของน้องๆนั่นเอง

พี่ๆได้รวบรวมข้อมูลทั้งหมดในการเดินทางรอบๆสถาบันไว้ทั้งหมดแล้ว ดังนั้น น้องๆจึงสามารถนำเอกสารนี้ไปศึกษาเส้นทางจากบ้านของน้องๆได้เลย!

หากน้องๆสงสัย สอบถามหรือคำแนะนำสามารถติดต่อกลับมาได้ที่ :

ธนกฤต อินทะนิยม (พี่บุ้ค)
Mobile :084-919-7743
Facebook : fb.com/Tanakit.1nt

พี่ๆจะขอบคุณเป็นอย่างมาก หากได้รับคำติชมเพื่อนำไปพัฒนาเอกสารในงานครั้งต่อๆไป

INDEX

แนะนำคณะ	Page 2
การเดินทางด้วยรถไฟ	Page 3
การเดินทางด้วยรถไฟฟ้า Airport Rail Link	Page 4
การเดินทางด้วยรถสองแถวและรถเมล์	Page 5
การเดินทางด้วยรถตู้ปรับอากาศ	Page 6
การเดินทางด้วยเครื่องบิน	Page 7
การเดินทางมาจากศูนย์ขนส่งสนามบินสุวรรณภูมิ	Page 8
การเดินทางมาคณะด้วยวิธีอื่นๆ	Page 9
ความปลอดภัยคืออันดับหนึ่ง	Page10
จุดนัดพบน้องๆ	Page11
Photo Gallery คลังภาพ	Page12

สแกนสิ รออะไรล่ะ:

มาแนะนำคณะกันก่อน



ก่อตั้งเมื่อ : ปี 2539

ที่อยู่ : คณะเทคโนโลยีสารสนเทศ สถาบันเทคโนโลยีพระจอมเกล้าเจ้าคุณทหารลาดกระบัง เลขที่ 1 ซอยฉลองกรุง 1 แขวงลาดกระบัง เขตลาดกระบัง กรุงเทพฯ 10520

พิกัด : 13°43 52″N 100°46 52″E

Website : it.kmitl.ac.th

เบอร์โทร : 02-723-4900

สแกนสิ รออะไรล่ะ

คณะเทคโนโลยีสารสนเทศ
สถาบันเทคโนโลยีพระจอมเกล้าเจ้าคุณทหารลาดกระบัง

การเดินทางด้วยรถไฟ

สแกนสิ รออะไรล่ะ:

(การเดินทางสุดคลาสสิก ของเด็กเทคโนฯ)

สถานีต้นทาง

Picture by : **Tanakit Intaniyom**



สถานีกรุงเทพ (หัวลำโพง)

สถานีชุมทางฉะเชิงเทรา

ตารางเดินรถไฟจากสถานีกรุงเทพ (หัวลำโพง)

การรถไฟแห่งประเทศไทย STATE RAILWAY OF THAILAND

สถานีต้นทาง กรุงเทพ สถานีปลายทาง หัวตะเข้ ตรวจสอบ

ลำดับ	เลขขบวนรถ	ประเภทรถ	กรุงเทพ ออก	หัวตะเข้ ถึง	กำหนดเวลาเดินรถ	ราคา
1	379	ธรรมดา	4:15	5:10	ขบวน " 379 "	ตรวจสอบ
2	275	ธรรมดา	5:55	7:02	ขบวน " 275 "	ตรวจสอบ
3	285	ธรรมดา	6:55	8:13	ขบวน " 285 "	ตรวจสอบ
4	283	ธรรมดา	6:55	8:13	ขบวน " 283 "	ตรวจสอบ
5	281	ธรรมดา	8:00	8:56	ขบวน " 281 "	ตรวจสอบ
6	367	ธรรมดา	10:10	11:08	ขบวน " 367 "	ตรวจสอบ
7	389	พิเศษชานเมือง	12:10	13:02	ขบวน " 389 "	ตรวจสอบ
8	279	ธรรมดา	13:05	13:47	ขบวน " 279 "	ตรวจสอบ
9	277	ธรรมดา	15:25	16:17	ขบวน " 277 "	ตรวจสอบ
10	391	พิเศษชานเมือง	16:55	17:51	ขบวน " 391 "	ตรวจสอบ
11	371	ธรรมดา	17:40	18:41	ขบวน " 371 "	ตรวจสอบ
12	383	ธรรมดา	18:25	19:23	ขบวน " 383 "	ตรวจสอบ
13	381	ธรรมดา	18:25	19:23	ขบวน " 381 "	ตรวจสอบ

ตารางเดินรถไฟจากสถานีชุมทางฉะเชิงเทรา

การรถไฟแห่งประเทศไทย STATE RAILWAY OF THAILAND

สถานีต้นทาง ชุมทางฉะเชิงเทรา สถานีปลายทาง หัวตะเข้ ตรวจสอบ

ลำดับ	เลขขบวนรถ	ประเภทรถ	ชุมทางฉะเชิงเทรา ออก	หัวตะเข้ ถึง	กำหนดเวลาเดินรถ	ราคา
1	384	ธรรมดา	5:45	6:25	ขบวน " 384 "	ตรวจสอบ
2	372	ธรรมดา	6:19	6:59	ขบวน " 372 "	ตรวจสอบ
3	388	พิเศษชานเมือง	7:05	7:34	ขบวน " 388 "	ตรวจสอบ
4	278	ธรรมดา	8:31	9:09	ขบวน " 278 "	ตรวจสอบ
5	280	ธรรมดา	10:22	11:06	ขบวน " 280 "	ตรวจสอบ
6	368	ธรรมดา	12:35	13:14	ขบวน " 368 "	ตรวจสอบ
7	390	พิเศษชานเมือง	14:05	14:34	ขบวน " 390 "	ตรวจสอบ
8	282	ธรรมดา	15:34	16:08	ขบวน " 282 "	ตรวจสอบ
9	286	ธรรมดา	16:20	17:05	ขบวน " 286 "	ตรวจสอบ
10	284	ธรรมดา	16:20	17:05	ขบวน " 284 "	ตรวจสอบ
11	276	ธรรมดา	18:00	18:41	ขบวน " 276 "	ตรวจสอบ

หมายเหตุ :

1. ขบวน 283/284 วิ่งเฉพาะวันจันทร์ถึงศุกร์

2. ขบวน 285/286 วิ่งเฉพาะวันเสาร์ อาทิตย์และวันหยุดพิเศษ

3. หากน้องๆไม่ได้ขึ้นจากสถานีต้นทาง สามารถเข้าไปได้ที่ http://www.railway.co.th/checktime/checktime.asp แล้วเลือกสถานีที่น้องต้องการขึ้นเป็นต้นทาง และเลือกสถานีปลายทางเป็น "หัวตะเข้" หรือ "พระจอมเกล้า" *หัวตะเข้ติดใกล้กว่า

4.ถ้าเลือกขึ้นไม่พบขบวนที่ต้องการ แสดงว่าน้องอาจจะเลือกสถานีที่ไม่ได้อยู่บนรถไฟสายตะวันออก

5. น้องๆสามารถตรวจสถานะของขบวนรถได้ที่ http://train.telecom.kmitl.ac.th/ ซึ่งเป็นของพี่ปี 4 คณะวิศวกรรมศาสตร์ หรือของการรถไฟได้ที่ http://58.181.223.158/srttts/view/

6. จะมีขบวนชานเมืองขบวน 376 มาจากรังสิต ซึ่งไม่ได้อยู่บนตาราง วิ่งเฉพาะวันจันทร์-ศุกร์ (ออกรังสิต 05.35 ถึงหัวตะเข้ 07.40)

*อัปเดตข้อมูลวันที่ 11/10/2017

การเดินทางด้วยรถไฟฟ้า Airport Rail Link

สแกนสิ รออะไรล่ะ

(รวดเร็ว ทันสมัย แอร์เย็นสบาย)

สถานีต้นทาง

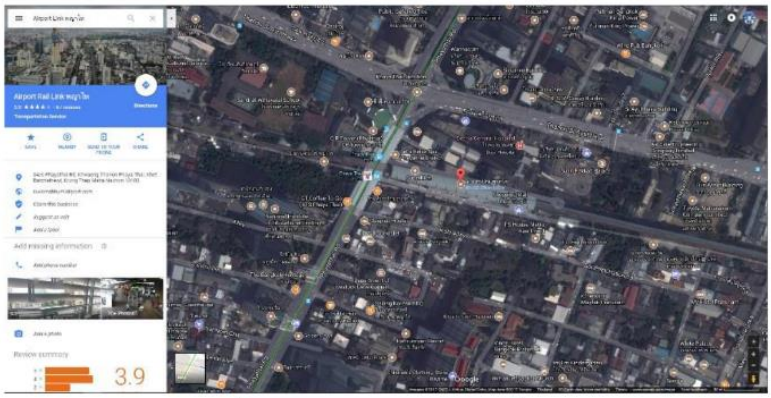

สถานีพญาไท

- เชื่อมต่อกับ BTS พญาไท
- เชื่อมต่อกับที่หยุดรถไฟพญาไท ของรถไฟสายตะวันออก

สถานีสุวรรณภูมิ

- เชื่อมต่อกับสนามบินสุวรรณภูมิ

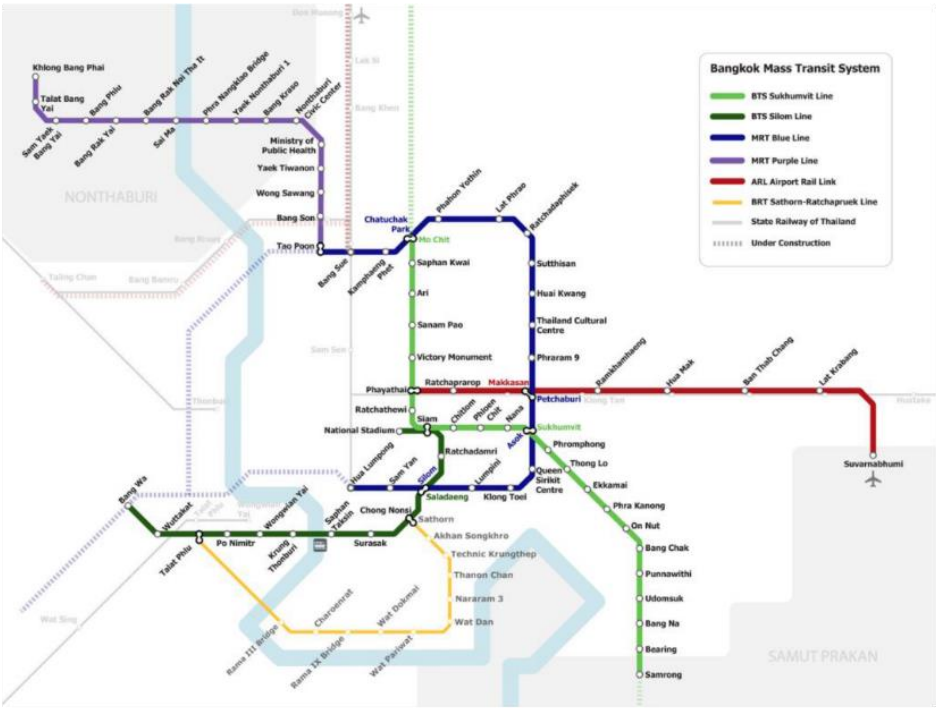

Reference
https://zh.wikipedia.org/wiki/File:BKK_masstransit_map_2016-01.png

หมายเหตุ

1. รถไฟฟ้า Airport Rail Link ให้บริการเวลา 06.00 – 24.00 ทุกวัน

2. หากน้องๆไม่ได้ขึ้นจากสถานีต้นทางสามารถตรวจสอบค่าโดยสารและเวลาการเดินทางได้ที่ http://www.srtet.co.th/

จากสถานีพญาไท

1. นั่งมาลงสถานีลาดกระบัง ค่าโดยสารอยู่ที่ 40 บาท

2. เมื่อลงสถานีลาดกระบังแล้ว ชั้นล่างสุดจะมีวินรถสองแถวอยู่ ให้น้องนั่งรถสองแถวสาย 777 (วงกลมเทคโนฯ) หรือหากนั่งไม่ถูก ให้สอบถามคนท้องถิ่นก็ได้ หรือจะรอพี่ๆมารับก็ได้ ***(ไปที่หน้า 11)*** (ถ้าบังเอิญจริงๆ ต่อรถไฟมาก็ได้นะ)

3. กดกริ่งลงคณะ IT ของเรา (จุดสังเกตคือเลยทางข้ามรถไฟกับพระบรมรูปรัชกาลที่ 4 มา 1 ป้ายรถเมล์)

จากสถานีสุวรรณภูมิ

1. ขึ้นลิฟท์ไปลงชั้นใต้ดินจากอาคารผู้โดยสาร จะมีป้ายเขียนบอกรถไฟฟ้าเข้าเมือง เดินไปตามป้าย

2. นั่งมาลงสถานีลาดกระบัง ค่าโดยสารอยู่ที่ 15 บาท

3. เมื่อลงสถานีลาดกระบังแล้ว ชั้นล่างสุดจะมีวินรถสองแถวอยู่ ให้น้องนั่งรถสองแถวสาย 777 (วงกลมเทคโนฯ) หรือหากนั่งไม่ถูก ให้สอบถามคนท้องถิ่นก็ได้ หรือจะรอพี่ๆมารับก็ได้ ***(ไปที่หน้า 11)***

4. กดกริ่งลงคณะ IT ของเรา (จุดสังเกตคือเลยทางข้ามรถไฟกับพระบรมรูปรัชกาลที่ 4 มา 1 ป้ายรถเมล์)

*อัปเดตข้อมูลวันที่ 11/10/2017

การเดินทางด้วยรถสองแถวและรถเมล์

(รับลมธรรมชาติ โหดบาร์สไตล์เด็กไอที)

สแกนสิ รออะไรละ

รถสองแถวในสถาบัน

รถเมล์หน้าตลาดหัวตะเข้

Picture by : **Tanakit Intaniyom**

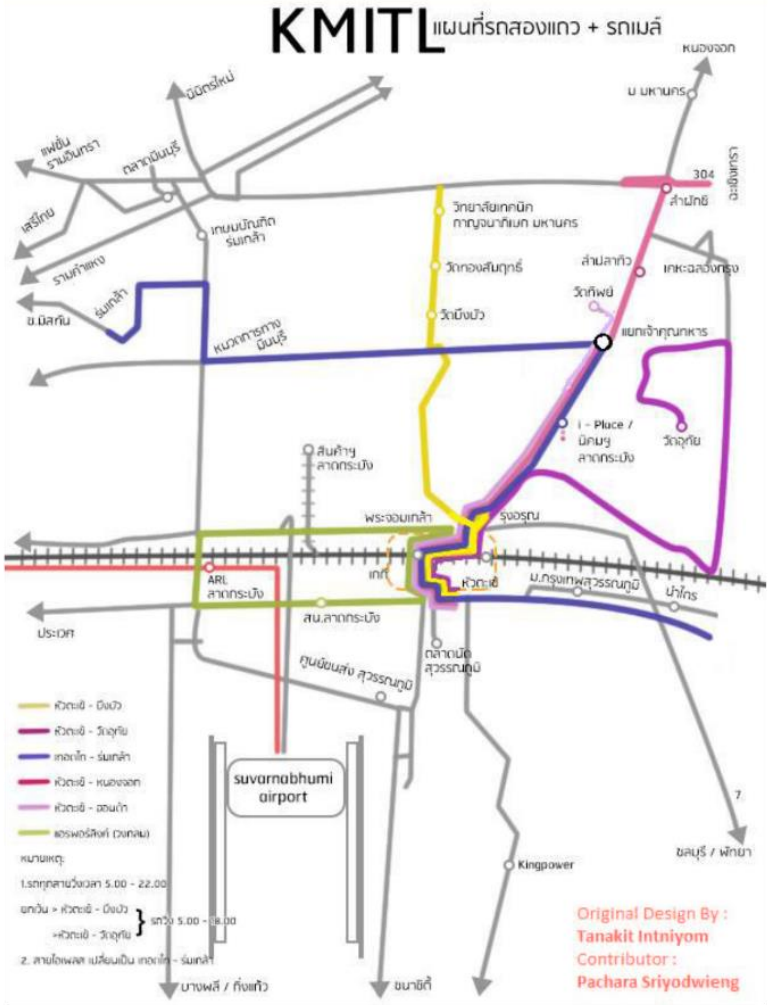

สองแถว (บริเวณในสถาบัน) **ดูแผนที่ด้านบน*

1. วงกลมวนซ้ายแอร์พอร์ตลิงค์	สีเขียว	7 บาท	5.00-22.00	15 นาที
2. หัวตะเข้ – เทคโน – หนองจอก	สีแดง	7 บาท	5.00-22.00	10 นาที
3. หัวตะเข้ – เทคโน – ฮอนด้า	สีชมพู	7 บาท	5.00-22.00	10 นาที
4. วัดราชโกษา – เทคโน – ร่มเกล้า	สีม่วง	7 บาท	5.00-20.00	20 นาที
5. หัวตะเข้ – เทคโน – วัดอุทัย	สีน้ำตาล	10 บาท	5.00-17.30	40 นาที
6. หัวตะเข้ – เทคโน – บึงบัว	สีเหลือง	10 บาท	5.00-17.30	30 นาที

รถสองแถว รถเมล์ และรถตู้ประจำทาง (บริเวณหน้าตลาดหัวตะเข้)

รถตู้ รถสองแถว และรถเมล์บริเวณนี้มีเยอะมากๆ น้องๆสามารถไปดาวโหลดเอกสารได้ที่

https://drive.google.com/file/d/0B7nrGLrf1Mk8OGZlTnVBbzRhQ2c/view?usp=sharing

*อัปเดตข้อมูลวันที่ 11/10/2017

การเดินทางด้วยรถตู้ปรับอากาศ

สแกนสิ รออะไรล่ะ:

(ปลากระป๋องแช่แข็ง)

รถตู้ประจำทางด่วนพิเศษ

รถตู้ประจำทาง

Picture by : **Tanakit Intaniyom**

สัญลักษณ์

สีเหลือง **ขอบเขตของสถาบัน**

สีแดง **ป้ายรถเมล์**

สีเขียว **ท่ารถตู้ด่วนพิเศษ**

รถสองแถว รถเมล์ และรถตู้ประจำทาง

น้องๆสามารถไปดาวโหลดเอกสารได้ที่

https://drive.google.com/file/d/0B7nrGLrf1Mk8OGZlTnVBbzRhQ2c/view?usp=sharing

รถตู้ประจำทาง สีแดง

1. หัวตะเข้ – หนองจอก
2. มีนบุรี – บึงบัว – หัวตะเข้
3. มีนบุรี – นิคม – หัวตะเข้
4. หัวตะเข้ – ซีคอนสแควร์*
5. ลาดกระบัง – ฉะเชิงเทรา*
6. หัวตะเข้ – บางพลี*

รถตู้ประจำทางด่วนพิเศษ สีเขียว

1. เทคโนฯลาดกระบัง – หมอชิต 2
2. เทคโนฯลาดกระบัง – อนุสาวรีย์ชัยฯ
3. เทคโนฯลาดกระบัง – รังสิต
4. เทคโนฯลาดกระบัง – แฮปปี้แลนด์

**ลงที่หน้าตลาดหัวตะเข้ รถไม่ได้เข้ามาภายในสถาบัน*

*อัปเดตข้อมูลวันที่ 11/10/2017

การเดินทางด้วยเครื่องบิน

สแกนสิ รออะไรละ:

(ว้าวว้าววว น้องว้าวมาได้!?)

สนามบินสุวรรณภูมิ

Picture by : **Tanakit Intaniyom**

จากสนามบินดอนเมือง

1. รถสาธารณะ

1.1 นั่งรถตู้ด่วนพิเศษสาย 555 สนามบินดอนเมือง – สนามบินสุวรรณภูมิ* **อ่านต่อด้านล่าง*

1.2 หรือรถเมล์สาย 554 / 555 รังสิต – สนามบินสุวรรณภูมิ (ขึ้นฝั่งเดียวกับสนามบิน)*

1.3 หรือเครื่องลงก่อนก่อนตี 5 ก็มารอรถไฟขบวน 376 รังสิต - หัวตะเข้ ได้เลย รถไฟออกดอนเมือง 05.45 (เฉพาะวันจันทร์-ศุกร์) แต่เอ๊ะ งานมันวันเสาร์-อาทิตย์นี่หน่า

2. รถบริการสนามบิน

รถสาย A1/A2 จะจอดบริเวณชั้น 1 ผู้โดยสารขาออก นั่งไปลง BTS หมอชิต หรือ MRT สวนจตุจักรแล้วต่อรถไฟฟ้า Airport Rail Link มา (กลับไปหน้า 4)

รถเมล์ด่วนสาย 555

จากสนามบินสุวรรณภูมิ

1. รถเมล์

1.1 บริเวณชั้น 1 จะมีป้ายรถเมล์อยู่ เดินออกมาข้างนอกประมาณ 100 เมตร รอรถเวียนสนามบิน รถเวียนทุกสาย (A/B/C/D/Express) ไปลงศูนย์ขนส่ง

/ จากสนามบินดอนเมือง */*

1.2 จากศูนย์ขนส่ง นั่งรถเวียนอีกต่อ (สาย C เท่านั้น) มาลงปากทางสุขสมาน (รถกลับรถเมื่อไหร่ก็ลงได้เลย)

1.3 เดินข้ามทางม้าลายมารอสองแถวสาย 777 (เขียนว่าเข้าเทคโนฯ) หรือจะนั่งวินมอเตอร์ไซค์บอกพี่ลงคณะไอทีก็ได้ (20 บาท)

2. รถไฟฟ้า

นั่งรถไฟฟ้า Airport Rail Link (ชั้นใต้ดิน) มาลงสถานีลาดกระบัง แล้วต่อรถสองแถวสาย 777 (วงกลมเทคโนฯ) กดกริ่งลงคณะไอที

รถเวียนภายในสนามบิน

Picture by : **Tanakit Intaniyom**

การเดินทางมาจากศูนย์ขนส่งสนามบินสุวรรณภูมิ

(มาสนามบิน แต่ไม่ได้ขึ้นเครื่องบิน)

สแกนสิ รออะไรล่ะ

บอร์ดตารางรถ



ภายในศูนย์ขนส่ง

Picture by : **Tanakit Intaniyom**

จากสถานที่ต่างๆ มาศูนย์ขนส่ง

1. รถตู้

/* 549 มีนบุรี – สุวรรณภูมิ

/* 552 อ่อนนุช - สุวรรณภูมิ

/* 552A ปากน้ำ – สุวรรณภูมิ (เฉพาะเช้า-เย็น)

/* 554 สะพานใหม่ – สุวรรณภูมิ (เฉพาะเช้า-เย็น)

/* 555 สุวรรณภูมิ - ดอนเมือง

/* 559 สุวรรณภูมิ – รังสิตฟิวเจอร์

2. รถเมล์

/* 554 รังสิต – สุวรรณภูมิ (ทางด่วนลงรามอินทรา)

/* 555 รังสิต – สุวรรณภูมิ (ทางด่วนลงดินแดง)

/* 558 พระราม 2 - สุวรรณภูมิ (ทางด่วนลงสุขสวัสดิ์)

***ยังมีรถเมล์ที่วิ่งระหว่างจังหวัดอีกแต่พี่ไม่ได้เก็บข้อมูลมา**

ศูนย์ขนส่งสนามบินสุวรรณภูมิ

หมายเหตุ :

1. หากน้องหลงอยู่ในสนามบิน อย่าพยายามที่จะเคลื่อนที่ไปไหน ให้อยู่กับที่เดิม แล้วโทรหาพี่ๆ ***(ไปที่หน้า 11)*** เพราะสนามบินมันกว้างมากๆ

2. หากน้องๆ ต้องการทราบเพิ่มเติมสามารถเข้าไปได้ที่ http://www.suvarnabhumiairport.com/th/1850-suvarnabhumi-bus-terminal

*อัปเดตข้อมูลวันที่ 11/10/2017

จากศูนย์ขนส่งไปคณะไอที

1. จากศูนย์ขนส่ง นั่งรถเวียนอีกต่อ (สาย C เท่านั้น) มาลงปากทางสุขสมาน (รถกลับรถเมื่อไหร่ก็ลงได้เลย)

2. เดินข้ามทางม้าลายมารอสองแถวสาย 777 (เขียนว่าเข้าเทคโนฯ) หรือจะนั่งวินมอเตอร์ไซค์บอกพี่ลงคณะไอทีก็ได้ (20 บาท)

การเดินทางมาคณะด้วยวิธีอื่นๆ

สแกนสิ รออะไรล่ะ

(คนจริง 2018)

บัตรทางด่วน รับก่อนจ่ายทีหลัง

รถแท็กซี่

Picture by : **Tanakit Intaniyom**

คณะเทคโนโลยีสารสนเทศ สถาบันเทคโนโลยีพระจอมเกล้าเจ้าคุณทหารลาดกระบัง

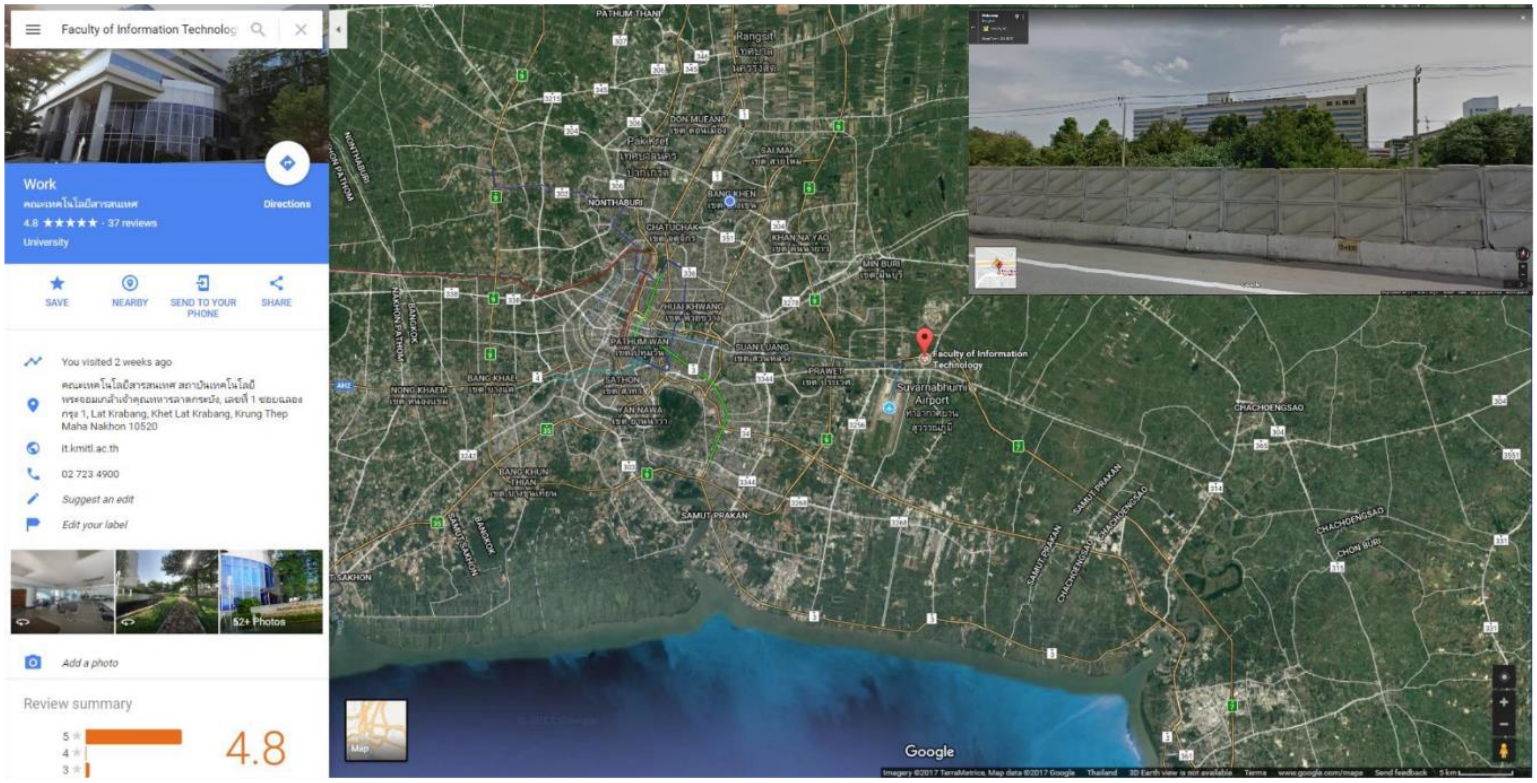

มาทางด่วนมอเตอร์เวย์ ง่ายที่สุด (ทั้งจากชลบุรี พัทยา และมักกะสัน)

เขียนว่าลง “เทคโนพระจอมเกล้าฯ” ก็ลงได้เลย

จะใช้แกนว้าปก็ได้นะ คณะเราติดตั้งที่...

นั่งเฮลิคอปเตอร์มาลงจุดจอด...

แท่น Jetpack จอดด้านฟ้า...

พี่ล้อเล่นหนะ ขำๆ

ความปลอดภัยคืออันดับหนึ่ง

สแกนสิ รออะไรล่ะ

(พี่ๆจะไม่ยอมให้น้องเป็นอะไรเด็ดขาด)

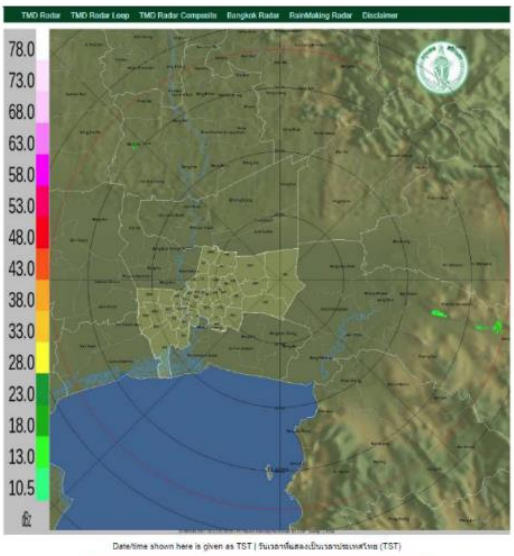

เรดาร์ฝนกรุงเทพ

สามารถตรวจสอบได้ที่ http://weather.tmd.go.th/bma_nck.php

ข่าวสารจาก Facebook

สามารถตรวจสอบได้ที่

https://www.facebook.com/groups/kmitltobeit/

รถตู้ประจำทาง

http://www.thaiemsinfo.com/autopagev4/show_page.php?topic_id=354&auto_id=7&TopicPk

เรือโดยสาร

https://today.line.me/th/pc/article/9a992a997c028f5adab940f38453a408dc1e99b26388b80056a22ca9773be165

รถไฟ

http://www.railway.co.th/main/knowledge/Instructions.html

Picture by : **Nathan Yiangsupapaanontr**

จุดนัดพบน้องๆ

สแกนสิ รออะไรล่ะ

(ถ้าน้องมาไม่ถูก พี่ๆจะแบกน้องไปคณะเอง)

หน้าคณะไอที

ท่ารถตู้ด่วนพิเศษ

สถานีรถไฟหัวตะเข้

โดยแต่ละจุดนั้นจะมีพี่ๆ คอยถือธงรอน้องๆอยู่ หากไม่พบให้รอตรงนั้นประมาณ **15 นาที** (เพราะพี่ๆอาจจะไปส่งน้องๆคนอื่นอยู่) ดังนั้นอย่าไปไหนนะครับ เดี๋ยวจะหลงทาง ถ้าในกรณีเร่งด่วน ให้โทรหาพี่ๆประจำจุดนั้นนะครับ

Picture by : **Tanakit Intaniyom**



สีเหลือง	หน้าคณะไอที
พี่สปาย	โทร 083-117-1875
สีส้ม	สถานีรถไฟหัวตะเข้
พี่โย๋ และพี่ใบปอ	โทร 083-711-7271 และ 095-112-2551
สีเขียว	ท่ารถตู้ด่วนพิเศษ
พี่ใบตอง	โทร 096-273-5807
สีม่วง	รถไฟฟ้า Airport Rail Link ลาดกระบัง
พี่บุ้ค	โทร 084-919-7743
สีฟ้า	Terminal สนามบินสุวรรณภูมิ และศูนย์ขนส่งสุวรรณภูมิ
พี่คิม	โทร 085-164-5705

Photo Gallery คลังภาพ

(มีอะไรสนใจบ้างไหมนะ)

สแกนสิ รออะไรล่ะ

Picture by : **Tanakit Intaniyom**



สุดท้ายนี้พี่ขอให้สนุกกับกิจกรรม ToBeIT#61 ติวก่อนสอบเพื่อน้องนะครับ
มีพี่ๆใจดีทุกคนดูแลน้องๆเป็นอย่างดี

หากน้องๆสงสัยเรื่องเส้นทาง สอบถามหรือคำแนะนำสามารถติดต่อกลับมาได้ที่ :

ธนกฤต อินทะนิยม (พี่บุ้ค)
Mobile : 084-919-7743
Facebook : fb.com/Tanakit.1nt

โชคดีนะครับ เดินทางปลอดภัยนะ

#ทีมงาน

ข้อมูลเส้นทาง ภาพถ่ายและจัดทำซีท :
ธนกฤต อินทะนิยม
สนับสนุนเทคนิค :
พีรดา มั่นศิลป์
ธัญชนก พัววิริยะกุล
วราภรณ์ พรมพลเมือง
แผนกขนส่ง :
พิชญุตม์ เดชหนู
โฆษิต โฆษิตศรีคุณากร

ID VERIFIED